서민을 따뜻하게 중산층을 두텁게

미래로 통하는 빛 통계청

http://kostat.go.kr

보도자료	2010. 8. 19(목) 조간부터 사용하시기 바랍니다.	
	배포일시	2010. 8. 18(수) 10:00
	담당부서	사회통계국 농어업통계과
	담 당 자	과 장 : 김봉철 (042.481.2583) 사무관 : 박재화 (042.481.3900)

2010년 벼, 고추 재배면적 조사 결과

❑ '10년 벼 재배면적은 전년보다 3.5% 감소

○ **('09)924,471 → ('10)892,074ha(-32,397ha, -3.5%)**

- '09년 논 면적 감소, 논 타작물 재배사업 추진 등에 기인
  - · 논벼 : ('09)917,990 → ('10)886,516ha(-31,474ha, -3.4%)
  - · 밭벼 : ('09) 6,481 → ('10) 5,558ha(-923ha, -14.2%)

〈연도별 벼 재배면적 추이〉

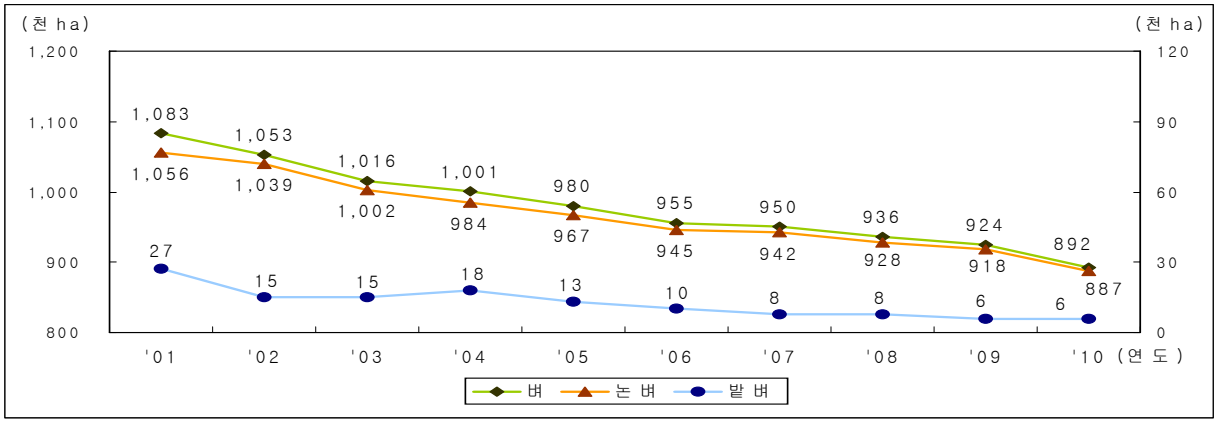

❑ '10년 고추 재배면적은 전년보다 0.5% 감소

○ **('09)44,817 → ('10)44,584ha(-233ha, -0.5%)**

- 농촌인구 고령화 및 노동력 부족, 인건비 상승 등으로 소폭 감소

Ⅰ. 2010년 벼, 고추 재배면적 조사결과

1. 벼 재배면적

'10년 벼 재배면적은 892,074ha로 '09년보다 32,397ha(3.5%) 감소
- 논벼 : ('09)917,990 → ('10)886,516ha(-31,474ha, -3.4%)
- 밭벼 : ('09) 6,481 → ('10) 5,558ha(-923ha, -14.2%)

○ 논벼의 경우,

- 형질변경, 건물건축 등으로 논 면적이 감소하였으며,
  * 논면적 변화추이 : ('07) 1,070 → ('08) 1,046 → ('09) 1,010천ha(-36천ha, -3.4%)
- 벼 적정 재배면적 유지를 위한 논에 타작물 재배사업 추진,
- 쌀 재고량 증가로 인한 쌀값하락에 대한 우려와 공공비축 미곡 매입 물량 감소 등으로 재배면적 감소
  * 쌀생산량 추이 : ('07)441 → ('08)484 → ('09)492(8만톤, 1.7%)
  * MMA 쌀 도입현황(농림수산식품부)
    : ('07년분)27 → ('08년분)29 → ('09년분)31 → ('10년분)33만톤(2만톤, 6.4%)
  * 공공비축 미곡 매입물량(농림수산식품부)
    : ('07)43 → ('08)40 → ('09)37 → ('10계획)34만톤(-3만톤, -8.1%)

○ 밭벼는 논벼에 비해 단위당 생산량이 떨어지고 정부의 고품질 쌀 생산을 위한 밭벼재배 억제시책 추진 등으로 재배면적 감소
  * 10a당 수량(논벼/밭벼) : ('07)466 / 240 → ('08)520 / 237 → ('09)534kg / 268kg

〈연도별 벼 재배면적 추이〉

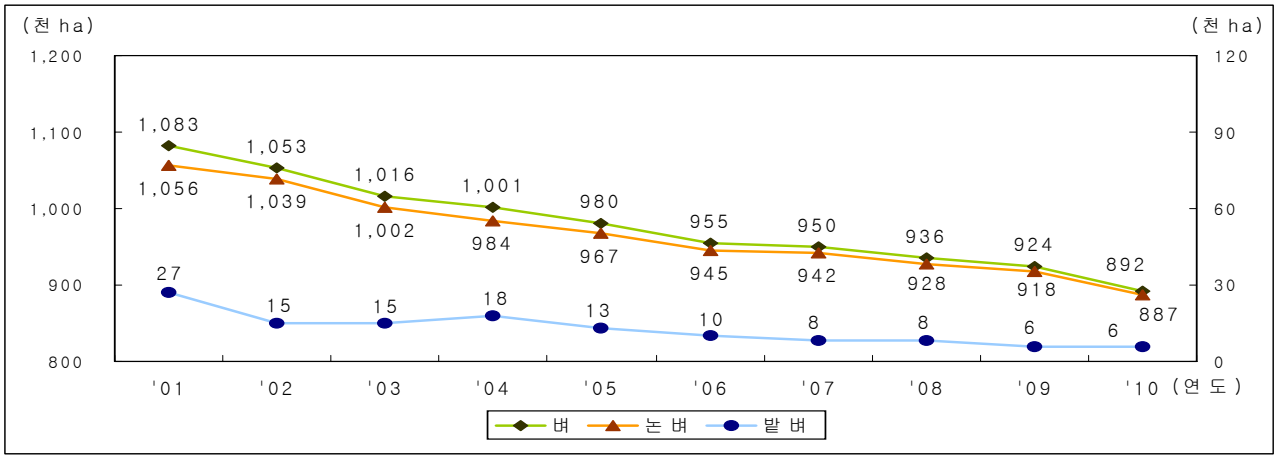

2. 고추 재배면적

'10년 고추 재배면적은 44,584ha로 '09년보다 233ha(0.5%) 감소

○ 지난해 생산량 감소로 가격이 좋아 단위면적당 소득 증가, 지리적 표시제 등록 등에 의한 기대심리로 일부 지역에서 재배면적을 늘렸으나

* 고추 생산량 : ('07)160 → ('08)124 → ('09)117천톤(-7천톤, -5.6%)
* 고추 도매가격(농수산물유통공사, 화건상품)
  : ('07)7,746 → ('08)9,515 → ('09)9,498원/kg(-17원, -0.2%)
* 고추 10a당 소득(농산물생산비조사)
  : ('07)1,793 → ('08)1,882 → ('09)2,001천원(119천원, 6.3%)

○ 고추는 노동력이 많이 필요한 작물이나 농촌인구 고령화 및 노동력 부족, 인건비 상승에 따라 전체적으로 재배면적이 소폭 감소

* 농가인구 고령화율(농업조사) : ('07)32.1 → ('08)33.3 → ('09)34.2%
* '09년 10a당 노동력투입시간(농산물생산비조사) : 고추 173.8, 참깨 50.9, 콩 26.2시간
* 여자농업노임(농가판매및구입가격조사)
  : ('07)40,967 → ('08)44,672 → ('09)47,032원(2,360원, 5.3%)

〈연도별 고추 재배면적 및 가격동향〉

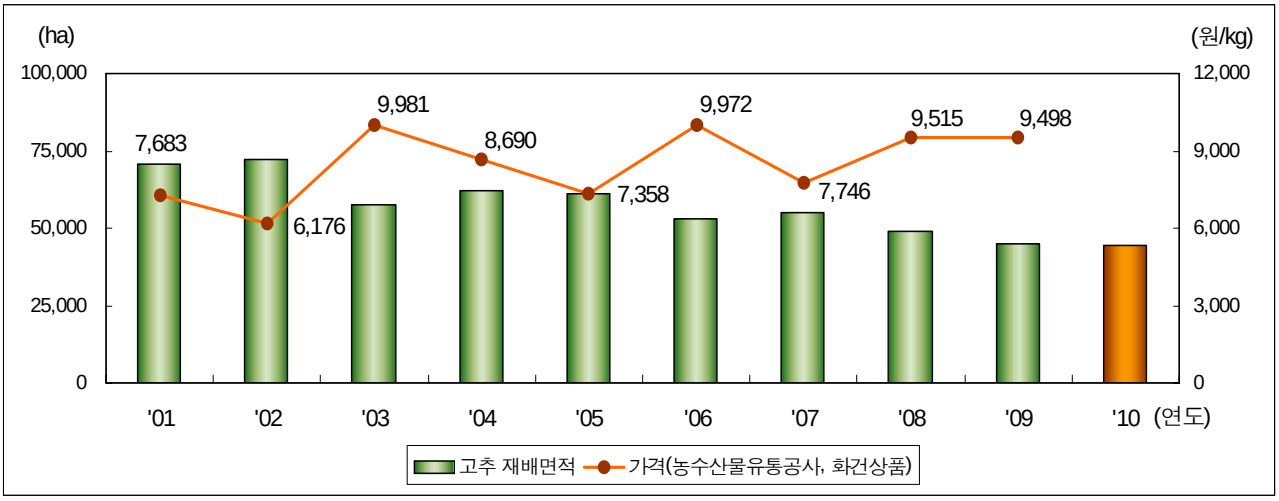

※ 가격은 8월부터 다음해 7월까지의 월평균 가격임

Ⅱ. 통계표

1. 벼

(단위 : ha, %)

	2009 재배면적 (A)	2010 재배면적 (B)	증 감	
			(B-A)	%
전 국	924,471	892,074	-32,397	-3.5
서 울	286	267	-19	-6.6
부 산	4,112	3,644	-468	-11.4
대 구	3,479	3,218	-261	-7.5
인 천	13,256	12,590	-666	-5.0
광 주	6,581	6,223	-358	-5.4
대 전	1,837	1,628	-209	-11.4
울 산	6,498	6,365	-133	-2.0
경 기	98,973	95,970	-3,003	-3.0
강 원	40,540	38,863	-1,677	-4.1
충 북	48,327	46,826	-1,501	-3.1
충 남	161,160	156,589	-4,571	-2.8
전 북	138,631	134,355	-4,276	-3.1
전 남	187,533	183,804	-3,729	-2.0
경 북	122,616	116,596	-6,020	-4.9
경 남	89,309	84,017	-5,292	-5.9
제 주	1,333	1,119	-214	-16.1

○ 논벼

(단위 : ha, %)

	2009 재배면적 (A)	2010 재배면적 (B)	증 감	
			(B-A)	%
전 국	917,990	886,516	-31,474	-3.4
서 울	286	267	-19	-6.6
부 산	4,112	3,644	-468	-11.4
대 구	3,477	3,217	-260	-7.5
인 천	13,256	12,588	-668	-5.0
광 주	6,528	6,182	-346	-5.3
대 전	1,837	1,628	-209	-11.4
울 산	6,480	6,341	-139	-2.1
경 기	98,934	95,894	-3,040	-3.1
강 원	40,420	38,809	-1,611	-4.0
충 북	48,257	46,758	-1,499	-3.1
충 남	160,952	156,456	-4,496	-2.8
전 북	138,445	134,123	-4,322	-3.1
전 남	183,359	180,163	-3,196	-1.7
경 북	122,441	116,472	-5,969	-4.9
경 남	89,181	83,950	-5,231	-5.9
제 주	25	24	-1	-4.0

○ **밭벼**

(단위 : ha, %)

	2009 재배면적 (A)	2010 재배면적 (B)	증 감	
			(B-A)	%
전 국	6,481	5,558	-923	-14.2
서 울	0	0	0	-
부 산	0	0	0	-
대 구	2	1	-1	-50.0
인 천	0	2	2	-
광 주	53	41	-12	-22.6
대 전	0	0	0	-
울 산	18	24	6	33.3
경 기	39	76	37	94.9
강 원	120	54	-66	-55.0
충 북	70	68	-2	-2.9
충 남	208	133	-75	-36.1
전 북	186	232	46	24.7
전 남	4,174	3,641	-533	-12.8
경 북	175	124	-51	-29.1
경 남	128	67	-61	-47.7
제 주	1,308	1,095	-213	-16.3

2. 고추

(단위 : ha, %)

	2009 재배면적 (A)	2010 재배면적 (B)	증 감	
			(B-A)	%
전 국	44,817	44,584	-233	-0.5
서 울	21	7	-14	-66.7
부 산	60	34	-26	-43.3
대 구	171	169	-2	-1.2
인 천	599	532	-67	-11.2
광 주	143	129	-14	-9.8
대 전	94	96	2	2.1
울 산	169	130	-39	-23.1
경 기	3,378	3,348	-30	-0.9
강 원	2,959	3,325	366	12.4
충 북	5,307	4,931	-376	-7.1
충 남	4,873	4,761	-112	-2.3
전 북	5,479	5,437	-42	-0.8
전 남	7,464	7,650	186	2.5
경 북	11,781	11,699	-82	-0.7
경 남	2,285	2,298	13	0.6
제 주	34	38	4	11.8

3. 논벼 주요 시군별 재배면적

(단위 : ha, %)

	2009 (A)	2010 (B)	증 감	
			(B-A)	(%)
경 기	98,934	95,894	-3,040	-3.1
평택시	14,643	14,362	-281	-1.9
고양시	1,698	1,525	-173	-10.2
시흥시	1,138	1,129	-9	-0.8
용인시	4,635	4,370	-265	-5.7
파주시	7,436	7,445	9	0.1
이천시	9,558	9,382	-176	-1.8
안성시	9,067	9,015	-52	-0.6
김포시	6,009	5,681	-328	-5.5
양주군	1,887	1,863	-24	-1.3
여주군	8,851	8,102	-749	-8.5
화성시	14,537	14,173	-364	-2.5
광주시	1,224	1,184	-40	-3.3
연천군	4,231	4,169	-62	-1.5
포천군	4,304	4,205	-99	-2.3
가평군	1,344	1,240	-104	-7.7
양평군	4,944	4,826	-118	-2.4
기 타	3,428	3,223	-205	-6.0

(단위 : ha, %)

	2009 (A)	2010 (B)	증 감	
			(B-A)	(%)
강 원	40,420	38,809	-1,611	-4.0
춘천시	2,196	2,082	-114	-5.2
원주시	4,177	4,104	-73	-1.7
강릉시	3,275	3,108	-167	-5.1
홍천군	3,886	3,657	-229	-5.9
횡성군	3,367	3,281	-86	-2.6
철원군	10,634	10,659	25	0.2
양구군	1,843	1,806	-37	-2.0
고성군	3,273	3,155	-118	-3.6
양양군	2,224	2,026	-198	-8.9
기 타	5,545	4,931	-614	-11.1
충 북	48,257	46,758	-1,499	-3.1
청주시	2,646	2,404	-242	-9.1
충주시	5,841	5,671	-170	-2.9
제천시	2,733	2,595	-138	-5.0
청원군	10,609	10,384	-225	-2.1
보은군	5,147	5,118	-29	-0.6
옥천군	2,638	2,542	-96	-3.6
영동군	1,952	1,671	-281	-14.4
진천군	5,347	5,268	-79	-1.5
괴산군	3,840	3,707	-133	-3.5
음성군	5,802	5,813	11	0.2
증평군	1,161	1,175	14	1.2
기 타	541	410	-131	-24.2

(단위 : ha, %)

	2009 (A)	2010 (B)	증 감 (B-A)	(%)
충 남	160,952	156,456	-4,496	-2.8
천안시	7,856	7,179	-677	-8.6
공주시	9,369	8,897	-472	-5.0
보령시	9,627	9,609	-18	-0.2
아산시	11,201	11,072	-129	-1.2
서산시	21,012	20,899	-113	-0.5
논산시	13,293	12,973	-320	-2.4
금산시	1,987	2,038	51	2.6
연기군	4,235	3,703	-532	-12.6
부여군	11,774	10,471	-1,303	-11.1
서천군	10,676	10,669	-7	-0.1
청양군	6,540	6,018	-522	-8.0
홍성군	9,868	9,955	87	0.9
예산군	11,867	11,962	95	0.8
태안군	10,081	9,851	-230	-2.3
당진군	21,294	20,883	-411	-1.9
기 타	272	277	5	1.8
전 북	138,445	134,123	-4,322	-3.1
전주시	3,285	2,961	-324	-9.9
군산시	13,139	13,113	-26	-0.2
익산시	19,299	18,303	-996	-5.2
정읍시	15,692	15,396	-296	-1.9
남원시	10,935	10,821	-114	-1.0
김제시	22,811	22,421	-390	-1.7
완주군	5,261	4,889	-372	-7.1
진안군	3,124	2,923	-201	-6.4
무주군	1,781	1,645	-136	-7.6
장수군	3,477	3,192	-285	-8.2
임실군	4,855	4,627	-228	-4.7
순창군	6,274	5,950	-324	-5.2
고창군	14,085	13,614	-471	-3.3
부안군	14,427	14,268	-159	-1.1

(단위 : ha, %)

	2009 (A)	2010 (B)	증 감	
			(B-A)	(%)
전 남	183,359	180,163	-3,196	-1.7
여수시	2,693	2,538	-155	-5.8
순천시	5,881	5,713	-168	-2.9
나주시	14,757	13,561	-1,196	-8.1
광양시	2,367	2,165	-202	-8.5
담양군	6,928	6,922	-6	-0.1
곡성군	5,452	5,286	-166	-3.0
구례군	3,454	3,249	-205	-5.9
고흥군	14,477	14,526	49	0.3
보성군	9,592	9,476	-116	-1.2
화순군	6,123	5,716	-407	-6.6
장흥군	9,259	8,892	-367	-4.0
강진군	10,257	10,159	-98	-1.0
해남군	20,547	22,223	1,676	8.2
영암군	16,381	15,916	-465	-2.8
무안군	9,416	9,366	-50	-0.5
함평군	8,763	8,567	-196	-2.2
영광군	11,083	10,845	-238	-2.1
장성군	5,974	5,475	-499	-8.4
완도군	2,993	2,745	-248	-8.3
진도군	6,693	6,693	0	0.0
신안군	9,997	9,913	-84	-0.8
기 타	272	217	-55	-20.2

(단위 : ha, %)

	2009 (A)	2010 (B)	증 감	
			(B-A)	(%)
경 북	122,441	116,472	-5,969	-4.9
포항시	8,343	8,317	-26	-0.3
경주시	14,154	13,810	-344	-2.4
김천시	5,658	5,430	-228	-4.0
안동시	7,020	6,444	-576	-8.2
구미시	7,800	5,851	-1,949	-25.0
영주시	5,328	5,114	-214	-4.0
영천시	4,293	4,017	-276	-6.4
상주시	14,257	13,887	-370	-2.6
문경시	5,273	5,159	-114	-2.2
경산시	1,619	1,525	-94	-5.8
군위군	2,661	2,778	117	4.4
의성군	11,129	11,121	-8	-0.1
청송군	1,474	1,362	-112	-7.6
영양군	1,149	1,174	25	2.2
영덕군	2,821	2,648	-173	-6.1
청도군	3,378	3,205	-173	-5.1
고령군	3,991	3,617	-374	-9.4
성주군	3,568	3,168	-400	-11.2
칠곡군	2,829	2,613	-216	-7.6
예천군	9,663	9,275	-388	-4.0
봉화군	3,236	3,284	48	1.5
울진군	2,797	2,673	-124	-4.4

(단위 : ha, %)

	2009 (A)	2010 (B)	증 감	
			(B-A)	(%)
경 남	89,181	83,950	-5,231	-5.9
창원시	3,332	2,739	-593	-17.8
마산시	1,417	1,322	-95	-6.7
진주시	6,262	6,113	-149	-2.4
사천시	5,182	4,848	-334	-6.4
김해시	5,544	4,672	-872	-15.7
밀양시	6,760	6,475	-285	-4.2
거제시	1,870	1,872	2	0.1
양산시	1,394	1,005	-389	-27.9
의령군	4,180	3,742	-438	-10.5
함안군	6,803	6,479	-324	-4.8
창녕군	6,999	6,610	-389	-5.6
고성군	6,687	6,483	-204	-3.1
남해군	3,141	3,097	-44	-1.4
하동군	5,489	5,390	-99	-1.8
산청군	4,498	4,521	23	0.5
함양군	4,483	4,292	-191	-4.3
거창군	5,698	5,540	-158	-2.8
합천군	8,778	8,219	-559	-6.4
기 타	664	531	-133	-20.0

Ⅲ. 작물재배면적조사 개요

□ 조사목적

○ 작물면적조사는 농산물수급안정 계획 수립, 농업정책 수행에 필요한 기초 자료를 수요자에게 제공하기 위해 실시

□ 조사연혁

○ 정부수립 이전부터 행정보고통계로 작성

○ 1967. 5. 29 지정통계로 지정

- 농업기본통계 및 경지면적조사 승인번호 11405호
- 작물재배면적조사 승인번호 11404호

○ 1973년에 표본설계를 하여 1974년부터 그간 실시해온 행정조사를 표본조사로 대체

○ 1987년, 1995년, 2006년 표본교체, 2008년 표본 일부 개편

○ 2008. 3. 5 통계청으로 이관

○ 2010년 경지면적조사와 통합 후 농업면적조사로 변경

□ 조사대상

○ '05년에 표본 설계된 931천여개의 모집단 조사구에서 추출된 24천여개의 표본 조사구

□ 조사기간 : 2010. 7. 5 ~ 7. 20(16일간)

□ 조사항목

○ 벼, 고추 등 전작물의 재배면적

□ 조사체계 및 방법

○ 통계청 농어업통계과 ↔ 지방청 및 사무소 ↔ 표본조사구

○ 현지를 방문하여 실측 또는 목측 조사

※ 수록된 자료(수치)는 사사오입 되었으므로 세목과 그 합계가 일치하지 않는 경우도 있으며, 단위에 따라 증감비율이 다를 수 있음

※ 아래의 텍스트를 클릭하면 지난 보도자료를 볼 수 있습니다.

지난 보도자료