보도자료	2011. 8. 23(화) 12시 부터 사용하시기 바랍니다.	
	배포일시	2011. 8. 23(화) 10:00
	담당부서	사회통계국 농어업통계과
	담 당 자	과 장 : 김봉철 (042.481.2583) 사무관 : 박재화 (042.481.3671)

2011년 벼, 고추 재배면적 조사 결과

❑ **'11년 벼 재배면적은 전년보다 4.3% 감소**

○ **('10)892,074 → ('11)853,823ha(-38,251ha, -4.3%)**

- '10년 논 면적 감소, 논 타작물 재배사업 추진 등에 기인

❑ **'11년 고추 재배면적은 전년보다 4.5% 감소**

○ **('10)44,584 → ('11)42,574ha(-2,010ha, -4.5%)**

- 농촌인구 고령화 및 노동력 부족, 단위면적(10a)당 소득 감소 등에 기인

〈연도별 벼, 고추 재배면적 추이〉

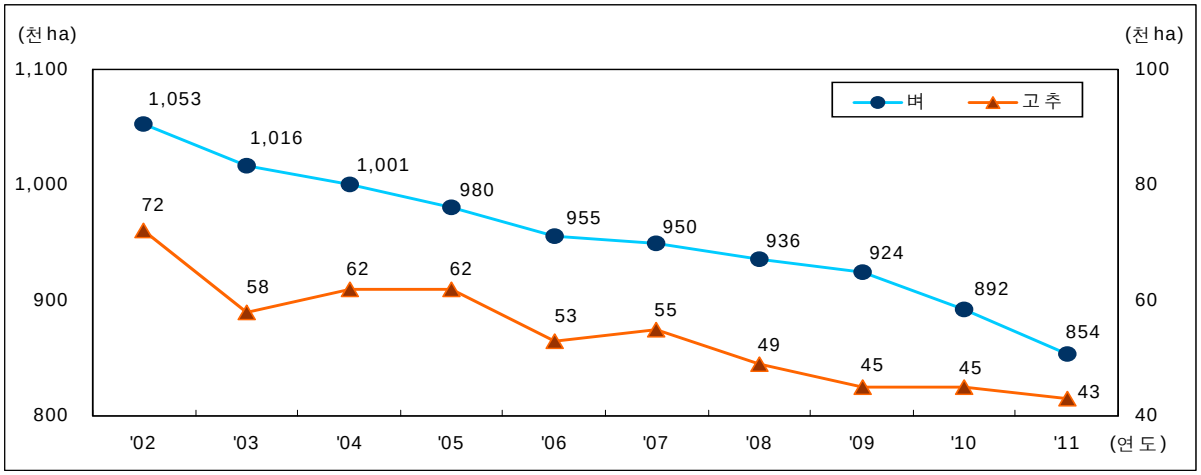

Ⅰ. 2011년 벼, 고추 재배면적 조사결과

1. 벼 재배면적

'11년 벼 재배면적은 853,823ha로 '10년보다 38,251ha(4.3%) 감소
- 논벼 : ('10)886,516 → ('11)850,798ha(-35,718ha, -4.0%)
- 밭벼 : ('10) 5,558 → ('11) 3,025ha(-2,533ha, -45.6%)

○ 논벼 재배면적이 감소한 이유는 형질변경, 건물건축, 유휴지 증가 등으로 논 면적이 감소하고,

* 논면적 변화추이 : ('08)1,046 → ('09)1,010 → ('10)984천ha(-26천ha, -2.6%)

○ 논에 벼 대신 다른 소득작물 재배를 유도하는 『'11년 논 소득기반 다양화 사업』 추진으로 콩, 대파, 옥수수, 사료작물 등 대체작물을 재배하여 면적 감소

* 논벼 대체작물 면적(농림수산식품부) : '10(실적)9.7천ha → '11(계획)40.0천ha

○ 밭벼는 논벼에 비해 단위당 생산량이 떨어지고, 고품질 쌀 생산을 위한 정부의 밭벼생산 감축사업 추진 등으로 재배면적 감소

* 10a당 생산량(논벼/밭벼) : ('08)520 / 237 → ('09)534 / 268 → ('10)483kg / 246kg

<연도별 벼 재배면적 추이>

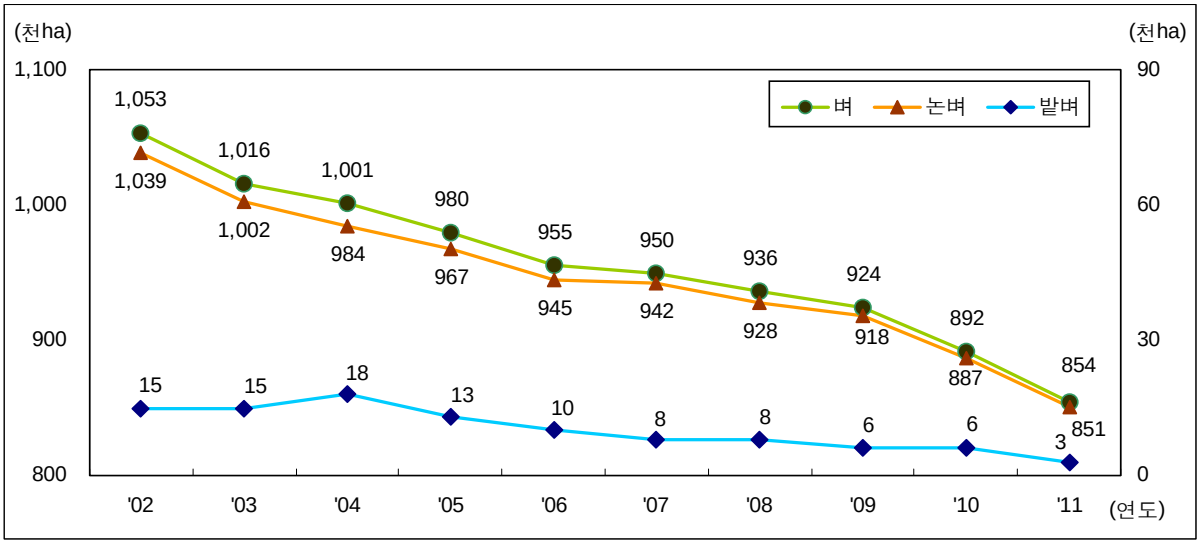

2. 고추 재배면적

'11년 고추 재배면적은 42,574ha로 '10년보다 2,010ha(4.5%) 감소

○ 고추는 노동력이 많이 필요한 작물이나 농촌인구 고령화 및 노동력 부족으로 재배면적이 지속적으로 감소하고 있으며,

* 농가인구 고령화율(농업조사) : ('07)32.1 → ('08)33.3 → ('09)34.2%

* '10년 10a당 노동력투입시간(농산물생산비조사) : 고추 167.6, 콩 25.8, 참깨 65.9시간
  · 참깨는 농촌진흥청의 '10 농축산물소득조사자료

○ 지난해 기상영향으로 인한 병충해 피해로 생산량이 크게 감소하여 가격은 좋았으나, 단위면적(10a)당 소득은 감소하여 이에 따른 영향으로 재배면적이 감소

* 고추 생산량 : ('08)124 → ('09)117 → ('10)95천톤(-22천톤, -18.8%)

* 고추 도매가격(농수산물유통공사, 화건상품)
  : ('08)9,515 → ('09)9,498 → ('10)13,801원/kg(4,303원, 45.3%)

* 고추 10a당 소득(농산물생산비조사)
  : ('08)1,882 → ('09)2,001 → ('10)1,523천원(-478천원, -23.9%)

〈연도별 고추 재배면적 및 가격동향〉

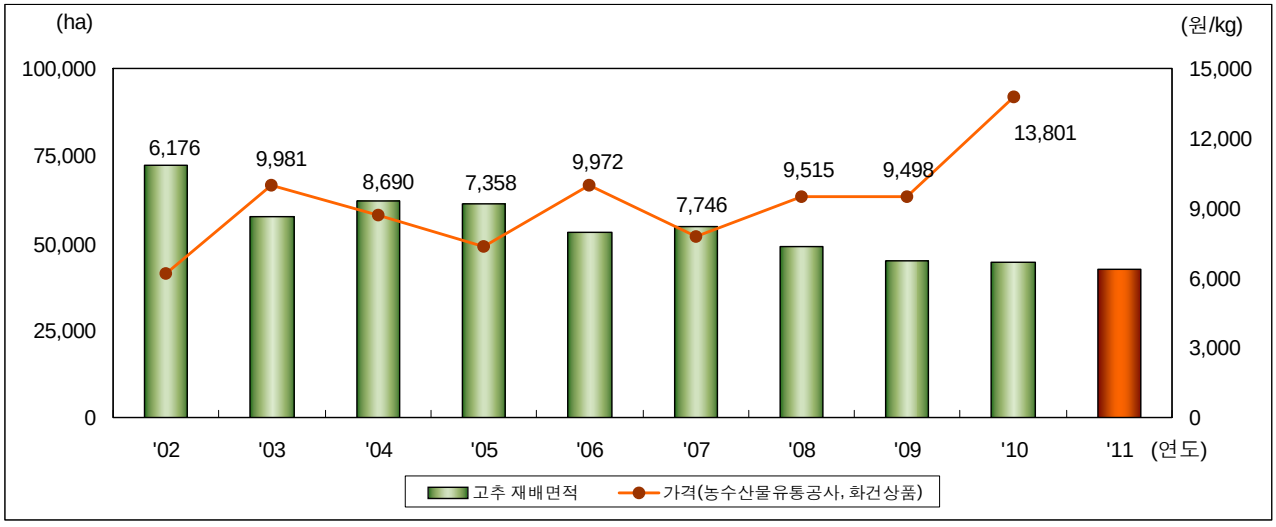

※ 가격은 8월부터 다음해 7월까지의 월평균 가격임

Ⅱ. 통계표

1. 벼

(단위 : ha, %)

	2010 재배면적(A)	2011 재배면적(B)	증 감 (B-A)	증 감 %
전 국	**892,074**	**853,823**	**-38,251**	**-4.3**
서 울	267	268	1	0.4
부 산	3,644	3,346	-298	-8.2
대 구	3,218	2,894	-324	-10.1
인 천	12,590	12,294	-296	-2.4
광 주	6,223	5,999	-224	-3.6
대 전	1,628	1,503	-125	-7.7
울 산	6,365	6,217	-148	-2.3
경 기	95,970	91,727	-4,243	-4.4
강 원	38,863	35,955	-2,908	-7.5
충 북	46,826	44,504	-2,322	-5.0
충 남	156,589	152,947	-3,642	-2.3
전 북	134,355	130,696	-3,659	-2.7
전 남	183,804	174,930	-8,874	-4.8
경 북	116,596	110,550	-6,046	-5.2
경 남	84,017	79,563	-4,454	-5.3
제 주	1,119	430	-689	-61.6

○ 논벼

(단위 : ha, %)

	2010 재배면적(A)	2011 재배면적(B)	증 감 (B-A)	%
전 국	**886,516**	**850,798**	**-35,718**	**-4.0**
서 울	267	268	1	0.4
부 산	3,644	3,346	-298	-8.2
대 구	3,217	2,890	-327	-10.2
인 천	12,588	12,294	-294	-2.3
광 주	6,182	5,952	-230	-3.7
대 전	1,628	1,503	-125	-7.7
울 산	6,341	6,213	-128	-2.0
경 기	95,894	91,689	-4,205	-4.4
강 원	38,809	35,914	-2,895	-7.5
충 북	46,758	44,480	-2,278	-4.9
충 남	156,456	152,861	-3,595	-2.3
전 북	134,123	130,549	-3,574	-2.7
전 남	180,163	172,842	-7,321	-4.1
경 북	116,472	110,458	-6,014	-5.2
경 남	83,950	79,522	-4,428	-5.3
제 주	24	17	-7	-29.2

2. 고추

(단위 : ha, %)

	2010 재배면적(A)	2011 재배면적(B)	증 감 (B-A)	증 감 %
전 국	**44,584**	**42,574**	**-2,010**	**-4.5**
서 울	7	8	1	14.3
부 산	34	58	24	70.6
대 구	169	160	-9	-5.3
인 천	532	552	20	3.8
광 주	129	116	-13	-10.1
대 전	96	92	-4	-4.2
울 산	130	169	39	30.0
경 기	3,348	3,129	-219	-6.5
강 원	3,325	3,016	-309	-9.3
충 북	4,931	4,588	-343	-7.0
충 남	4,761	4,428	-333	-7.0
전 북	5,437	5,432	-5	-0.1
전 남	7,650	7,265	-385	-5.0
경 북	11,699	10,896	-803	-6.9
경 남	2,298	2,628	330	14.4
제 주	38	37	-1	-2.6

3. 연도별 벼, 고추 재배면적 및 생산량

벼(쌀)				고 추			
연도	벼 재배면적	쌀 10a당 생산량	쌀 생산량	연도	재배면적	10a당 생산량	생산량
	ha	kg	천톤	단위	ha	kg	톤
‘90	1,244,341	451	5,606	’90	62,759	212	132,748
‘91	1,208,455	446	5,384	’91	70,919	199	141,320
‘92	1,156,885	461	5,331	’92	77,178	223	171,790
‘93	1,135,812	418	4,750	’93	85,221	219	187,043
‘94	1,102,608	459	5,060	’94	88,871	198	176,269
‘95	1,055,868	445	4,695	’95	87,469	221	193,331
‘96	1,049,556	507	5,323	’96	90,762	241	218,462
‘97	1,052,395	518	5,450	’97	77,549	259	200,705
‘98	1,058,927	482	5,097	’98	65,344	224	146,640
‘99	1,066,203	495	5,263	’99	75,574	285	215,382
‘00	1,072,363	497	5,291	’00	74,471	260	193,786
‘01	1,083,125	516	5,515	’01	70,736	255	180,120
‘02	1,053,186	471	4,927	’02	72,104	267	192,753
‘03	1,016,030	441	4,451	’03	57,502	230	132,010
‘04	1,001,159	504	5,000	’04	61,894	250	154,962
‘05	979,717	490	4,768	’05	61,299	263	161,380
‘06	955,229	493	4,680	’06	53,097	220	116,914
‘07	950,250	466	4,408	’07	54,876	292	160,398
‘08	935,766	520	4,843	’08	48,825	253	123,508
‘09	924,471	534	4,916	’09	44,817	262	117,324
‘10	892,074	483	4,295	’10	44,584	214	95,391
‘11	853,823	-	-	’11	42,574	-	-

4. 논벼 주요 시군별 재배면적

(단위 : ha, %)

	2010	2011	증 감	
	재배면적(A)	재배면적(B)	(B-A)	%
경기도	**95,894**	**91,689**	**-4,205**	**-4.4**
평택시	14,362	13,689	-673	-4.7
고양시	1,525	1,552	27	1.8
시흥시	1,129	1,074	-55	-4.9
용인시	4,370	4,379	9	0.2
파주시	7,445	7,128	-317	-4.3
이천시	9,382	8,768	-614	-6.5
안성시	9,015	8,424	-591	-6.6
김포시	5,681	5,297	-384	-6.8
화성시	14,173	13,922	-251	-1.8
광주시	1,184	967	-217	-18.3
양주시	1,863	1,791	-72	-3.9
포천시	4,205	3,743	-462	-11.0
여주군	8,102	8,137	35	0.4
연천군	4,169	3,876	-293	-7.0
가평군	1,240	1,144	-96	-7.7
양평군	4,826	4,678	-148	-3.1
기 타	3,223	3,120	-103	-3.2

(단위 : ha, %)

	2010 재배면적(A)	2011 재배면적(B)	증 감 (B-A)	증 감 %
강 원	**38,809**	**35,914**	**-2,895**	**-7.5**
춘천시	2,082	1,758	-324	-15.6
원주시	4,104	3,845	-259	-6.3
강릉시	3,108	2,864	-244	-7.9
홍천군	3,657	3,454	-203	-5.6
횡성군	3,281	3,225	-56	-1.7
철원군	10,659	10,214	-445	-4.2
양구군	1,806	1,601	-205	-11.4
고성군	3,155	2,903	-252	-8.0
양양군	2,026	1,982	-44	-2.2
기타	4,931	4,068	-863	-17.5
충 북	**46,758**	**44,480**	**-2,278**	**-4.9**
청주시	2,404	2,328	-76	-3.2
충주시	5,671	5,468	-203	-3.6
제천시	2,595	2,616	21	0.8
청원군	10,384	9,838	-546	-5.3
보은군	5,118	4,705	-413	-8.1
옥천군	2,542	2,369	-173	-6.8
영동군	1,671	1,468	-203	-12.1
진천군	5,268	5,139	-129	-2.4
괴산군	3,707	3,618	-89	-2.4
음성군	5,813	5,481	-332	-5.7
증평군	1,175	1,089	-86	-7.3
기 타	410	361	-49	-12.0

(단위 : ha, %)

	2010 재배면적(A)	2011 재배면적(B)	증 감 (B-A)	%
충 남	**156,456**	**152,861**	**-3,595**	**-2.3**
천안시	7,179	6,816	-363	-5.1
공주시	8,897	8,440	-457	-5.1
보령시	9,609	9,335	-274	-2.9
아산시	11,072	11,093	21	0.2
서산시	20,899	20,544	-355	-1.7
논산시	12,973	12,677	-296	-2.3
금산시	2,038	1,617	-421	-20.7
연기군	3,703	3,439	-264	-7.1
부여군	10,471	9,901	-570	-5.4
서천군	10,669	10,515	-154	-1.4
청양군	6,018	5,938	-80	-1.3
홍성군	9,955	9,909	-46	-0.5
예산군	11,962	11,928	-34	-0.3
태안군	9,851	9,899	48	0.5
당진군	20,883	20,537	-346	-1.7
기 타	277	273	-4	-1.4
전 북	**134,123**	**130,549**	**-3,574**	**-2.7**
전주시	2,961	2,773	-188	-6.3
군산시	13,113	12,996	-117	-0.9
익산시	18,303	18,133	-170	-0.9
정읍시	15,396	15,164	-232	-1.5
남원시	10,821	10,645	-176	-1.6
김제시	22,421	21,861	-560	-2.5
완주군	4,889	4,675	-214	-4.4
진안군	2,923	2,668	-255	-8.7
무주군	1,645	1,402	-243	-14.8
장수군	3,192	3,120	-72	-2.3
임실군	4,627	4,378	-249	-5.4
순창군	5,950	5,631	-319	-5.4
고창군	13,614	13,118	-496	-3.6
부안군	14,268	13,985	-283	-2.0

(단위 : ha, %)

	2010	2011	증 감	
	재배면적(A)	재배면적(B)	(B-A)	%
전 남	**180,163**	**172,842**	**-7,321**	**-4.1**
여수시	2,538	2,256	-282	-11.1
순천시	5,713	5,215	-498	-8.7
나주시	13,561	13,142	-419	-3.1
광양시	2,165	1,560	-605	-27.9
담양군	6,922	6,421	-501	-7.2
곡성군	5,286	5,034	-252	-4.8
구례군	3,249	3,161	-88	-2.7
고흥군	14,526	14,038	-488	-3.4
보성군	9,476	9,087	-389	-4.1
화순군	5,716	5,478	-238	-4.2
장흥군	8,892	8,929	37	0.4
강진군	10,159	9,922	-237	-2.3
해남군	22,223	21,561	-662	-3.0
영암군	15,916	15,485	-431	-2.7
무안군	9,366	8,882	-484	-5.2
함평군	8,567	8,170	-397	-4.6
영광군	10,845	10,756	-89	-0.8
장성군	5,475	5,363	-112	-2.0
완도군	2,745	2,762	17	0.6
진도군	6,693	5,720	-973	-14.5
신안군	9,913	9,703	-210	-2.1
기타	217	197	-20	-9.2

(단위 : ha, %)

	2010	2011	증 감	
	재배면적(A)	재배면적(B)	(B-A)	%
경 북	**116,472**	**110,458**	**-6,014**	**-5.2**
포항시	8,317	8,031	-286	-3.4
경주시	13,810	13,569	-241	-1.7
김천시	5,430	5,105	-325	-6.0
안동시	6,444	5,761	-683	-10.6
구미시	5,851	5,656	-195	-3.3
영주시	5,114	4,987	-127	-2.5
영천시	4,017	3,801	-216	-5.4
상주시	13,887	13,359	-528	-3.8
문경시	5,159	4,982	-177	-3.4
경산시	1,525	1,493	-32	-2.1
군위군	2,778	2,685	-93	-3.3
의성군	11,121	10,650	-471	-4.2
청송군	1,362	1,261	-101	-7.4
영양군	1,174	932	-242	-20.6
영덕군	2,648	2,266	-382	-14.4
청도군	3,205	3,033	-172	-5.4
고령군	3,617	3,312	-305	-8.4
성주군	3,168	3,013	-155	-4.9
칠곡군	2,613	2,442	-171	-6.5
예천군	9,275	8,566	-709	-7.6
봉화군	3,284	3,014	-270	-8.2
울진군	2,673	2,540	-133	-5.0

(단위 : ha, %)

	2010 재배면적(A)	2011 재배면적(B)	증 감 (B-A)	%
경 남	**83,950**	**79,522**	**-4,428**	**-5.3**
진주시	6,113	5,931	-182	-3.0
사천시	4,848	4,669	-179	-3.7
김해시	4,672	4,410	-262	-5.6
밀양시	6,475	6,082	-393	-6.1
거제시	1,872	1,861	-11	-0.6
양산시	1,005	1,008	3	0.3
창원시	4,186	3,893	-293	-7.0
의령군	3,742	3,681	-61	-1.6
함안군	6,479	6,096	-383	-5.9
창녕군	6,610	6,232	-378	-5.7
고성군	6,483	6,181	-302	-4.7
남해군	3,097	3,061	-36	-1.2
하동군	5,390	5,024	-366	-6.8
산청군	4,521	4,209	-312	-6.9
함양군	4,292	3,846	-446	-10.4
거창군	5,540	5,237	-303	-5.5
합천군	8,219	7,739	-480	-5.8
기 타	406	362	-44	-10.8

Ⅲ. 작물재배면적조사 개요

□ 조사목적

○ 작물면적조사는 농산물수급안정 계획 수립, 농업정책 수행에 필요한 기초 자료를 수요자에게 제공하기 위해 실시

□ 조사연혁

○ 정부수립 이전부터 행정보고통계로 작성

○ 1967. 5. 29 지정통계로 지정

- 작물재배면적조사 승인번호 11404호

○ 1974년부터 행정조사를 표본조사로 대체

○ 2008. 3. 5 통계청으로 이관

○ 2010년 경지면적조사와 통합 후 농업면적조사로 변경

□ 조사대상

○ 931천여개의 모집단 조사구에서 추출된 약 24천개의 표본 조사구

□ 조사기간 : 2011. 7. 5 ~ 7. 20(16일간)

□ 조사항목

○ 벼, 고추 등 전작물의 재배면적

□ 조사체계 및 방법

○ 통계청 농어업통계과 ↔ 지방청 및 사무소 ↔ 표본조사구

○ 현지를 방문하여 실측 또는 목측 조사

※ 수록된 자료(수치)는 사사오입 되었으므로 세목과 그 합계가 일치하지 않는 경우도 있으며, 단위에 따라 증감비율이 다를 수 있음